ROTA SEGURA

ADS, App World

Informações do APP

ROTA SEGURA



OBJETIVO

Proporcionar um **deslocamento seguro** nos grandes centros urbanos ao considerar dados e informações dos principais **indicadores de criminalidade por posição geográfica** ao longo do percurso. A plataforma oferece **rotas alternativas**, indica **melhores horários** para os deslocamentos e dá oportunidade e considera **a troca de informações** disponibilizadas pelos usuários da aplicação.

A base do serviço conta com uma **poderosa IA** que coleta, organiza e trabalha as informações em variados indicadores de criminalidade para **minimizar os riscos dos deslocamentos** dos usuários.

Trata-se de um protótipo de um serviço que poderá ser adquirido pelas diferentes plataformas de geolocalização.

APLICAÇÃO

A aplicação é baseada:

Guia de início rápido do SDK do Maps para Android | Google for Developers

Telas

INTERFACE COM O USUÁRIO

TELA 1

Tela de Login

Com escolha do método e mensagem de saudação

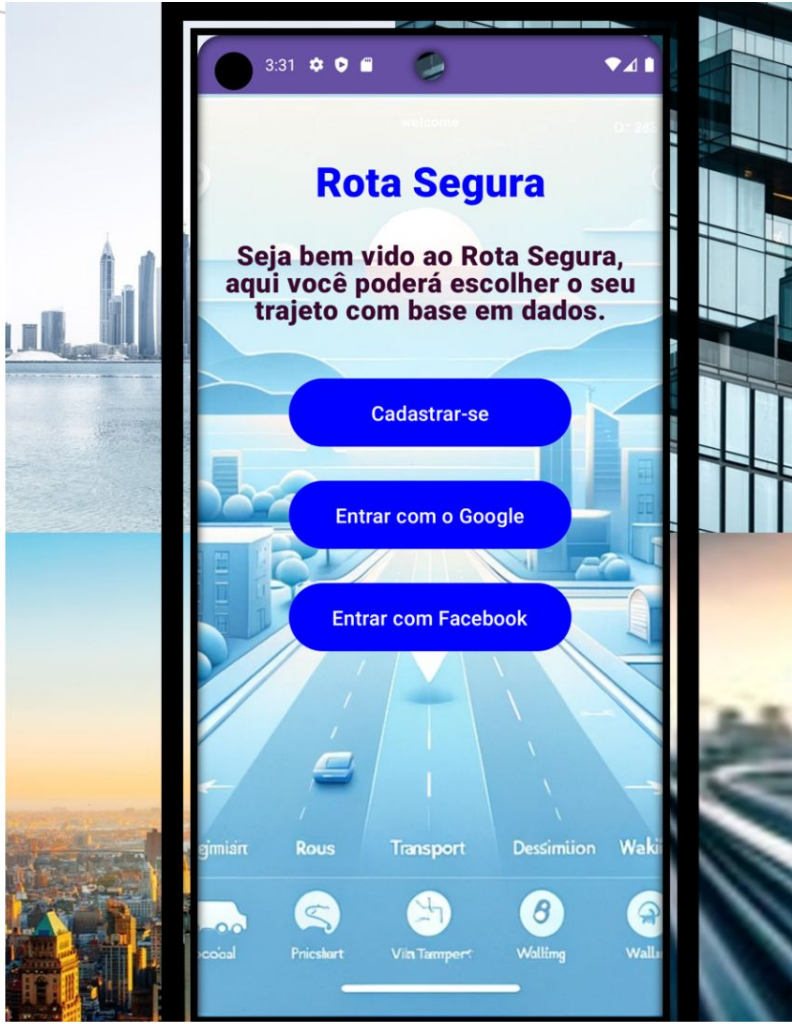

TELA 2

Operacionalização do Login

Opção de login com Facebook

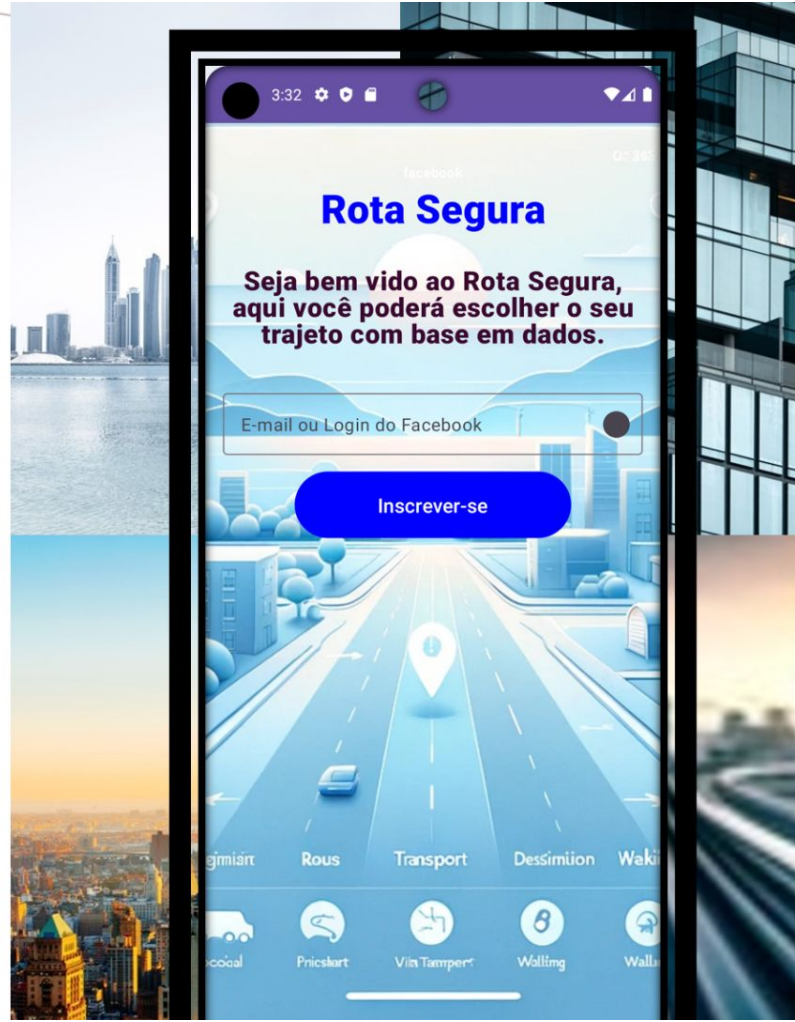

TELA 3

Tela de serviços do App

Percurso e trajeto (API Google Maps)

Relatório de Segurança

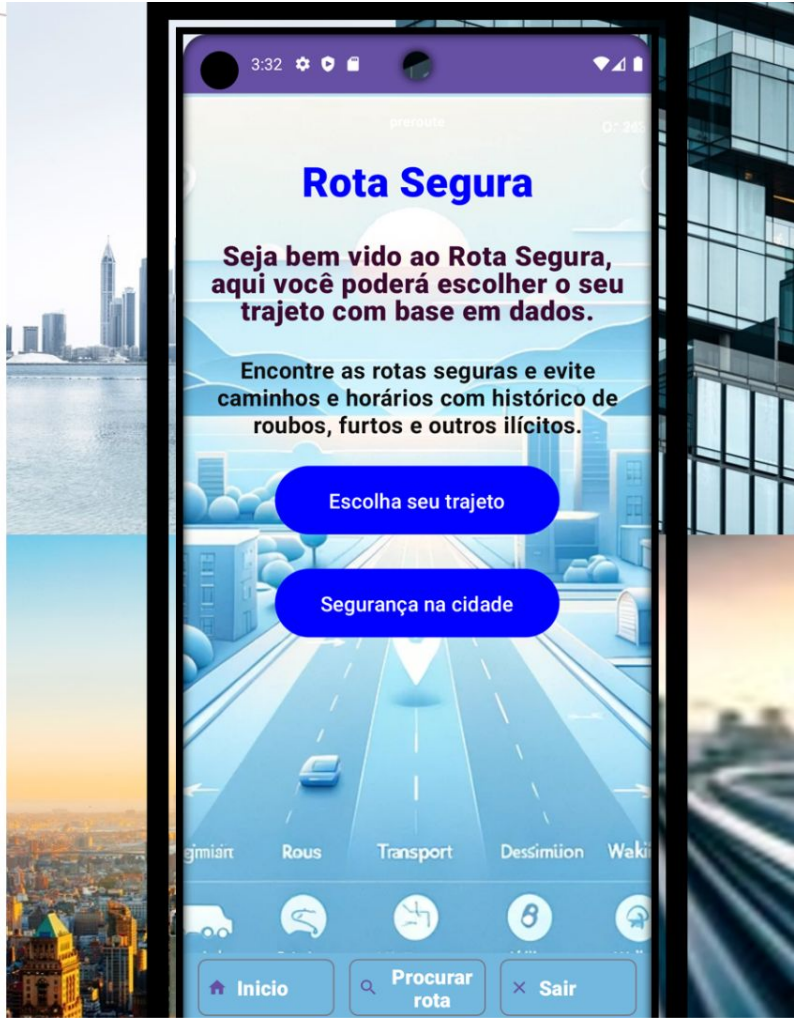

TELA 4

Exibição do Mapa

Renderização do Mapa (Google Maps)

Polígonos do Perigo (a desenvolver)

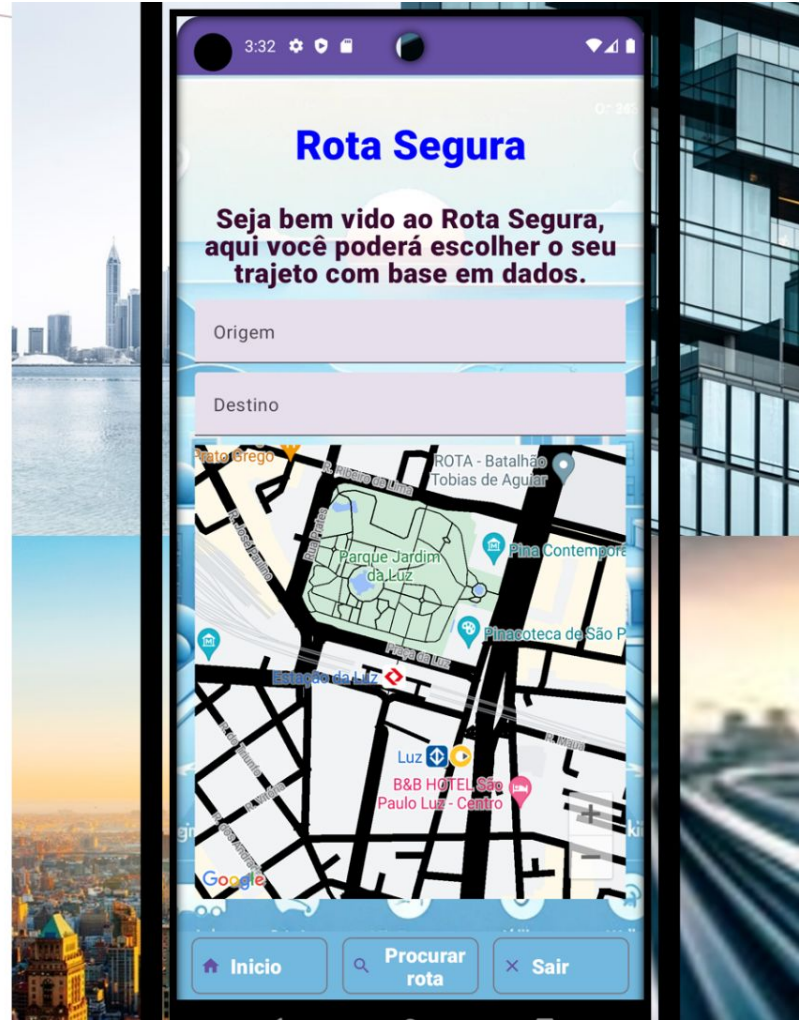

TELA 5

Relatório Segurança

Relatório com diagnóstico, classificação e apontamentos relativos à segurança do percurso ou de localizações geográficas específicas (bairros, logradouros, CEP etc).

[Em construção...]



PRÓXIMOS PASSOS

E para por aqui...

APP - ROTA SEGURA

- Dados e informações para apuração do risco deslocamento: Secretaria de Segurança Pública Estadual, Ministério da Justiça, Detran etc.
- O usuário tem a oportunidade de interagir e contribuir com novas e qualificadas informações.
- Os dados são tratados numa poderosa IA hospedada em serviços de cloud.
- A plataforma conta com “curadoria” das informações e dados compartilhados.